Nr	Y	X	H	Kodi	Përshkrimi	Burimi
2	7508341.840	4696777.923	606.713	40	Shtëpi-Ndërtesë	PM
6	7508337.302	4696773.278	606.713	40	Shtëpi-Ndërtesë	PM
17	7508329.215	4696780.387	606.713	40	Shtëpi-Ndërtesë	PM
20	7508328.464	4696776.214	606.713	40	Shtëpi-Ndërtesë	PM
21	7508327.580	4696776.373	606.713	40	Shtëpi-Ndërtesë	PM
24	7508327.112	4696773.824	606.713	40	Shtëpi-Ndërtesë	PM
25	7508327.996	4696773.674	606.713	40	Shtëpi-Ndërtesë	PM
35	7508340.865	4696772.544	606.713	40	Shtëpi-Ndërtesë	PM
37	7508336.678	4696769.938	606.713	40	Shtëpi-Ndërtesë	PM
38	7508336.362	4696769.982	606.713	40	Shtëpi-Ndërtesë	PM
39	7508334.951	4696769.015	606.713	40	Shtëpi-Ndërtesë	PM
40	7508333.108	4696769.414	606.713	40	Shtëpi-Ndërtesë	PM
41	7508332.215	4696770.638	606.713	40	Shtëpi-Ndërtesë	PM
43	7508331.794	4696770.895	606.713	40	Shtëpi-Ndërtesë	PM
44	7508327.626	4696771.688	606.713	40	Shtëpi-Ndërtesë	PM

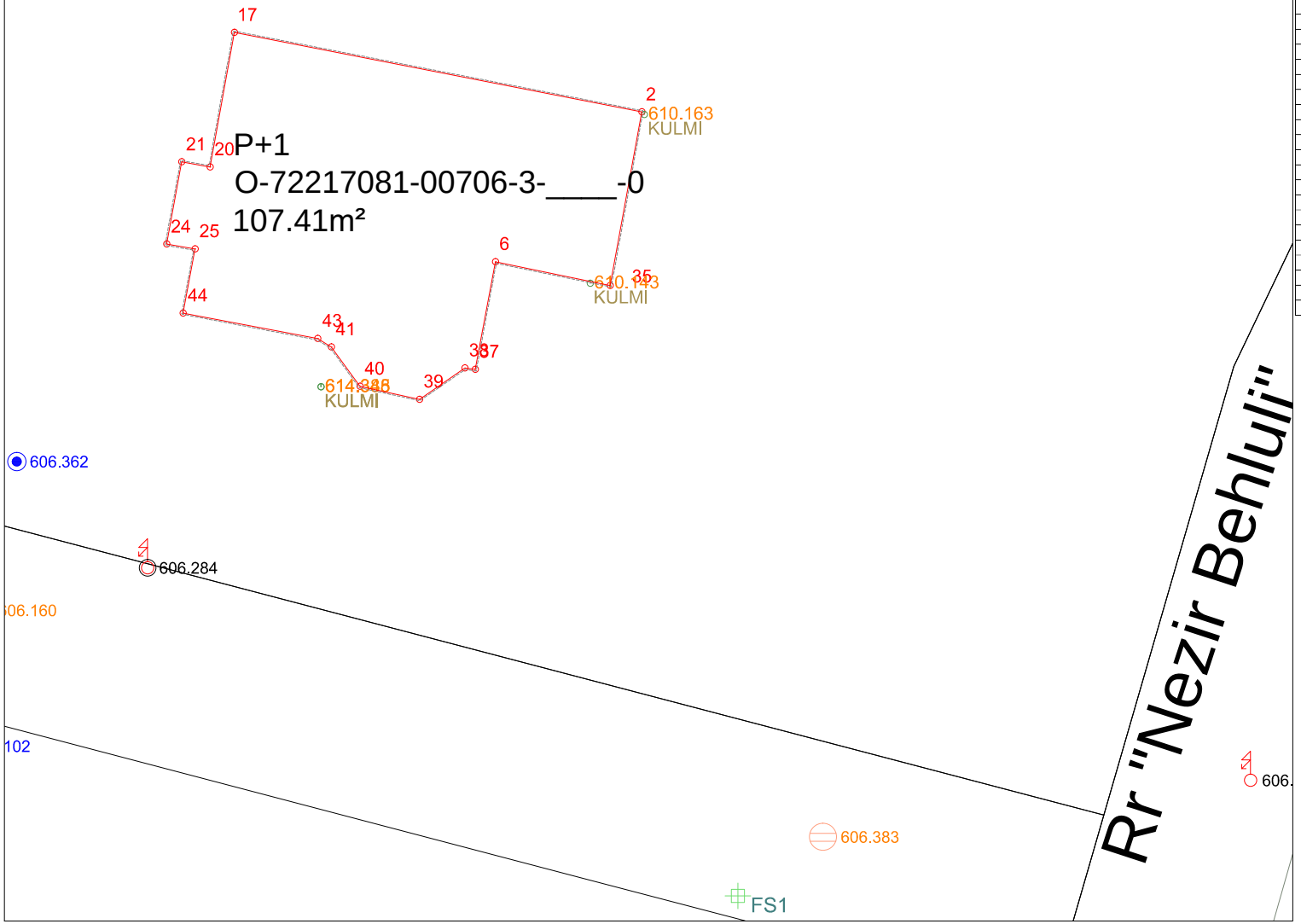

Republika e Kosovës

Qeveria -Vlada

Ministria e Mjedisit dhe Planifikimit Hapësinr /Ministarstv Sredine i Prstrng Planiranja

AGJENCIA KADASTRALE E KOSOVËS/ KATASTARSKA AGENCIJA KOSOVA

Situacioni i terrenit

Zyra kadastrale kmunale / pštinska katastarska kancelarija: Ferizaj

Zona kadastrale / Katastarska zona: Slivovë

Nr. i njësisë kadastrale / Br. katastarske jedinice : 706-3

Numri i lëndës / Broj predmeta: _____

Shkalla e zvoglimit / Razmera plana 1: 200

Lista e koordinatave të pikave të matura:

Nr	Y	X	H	DSC
319	7508342.699	4696784.165	606.735	BUNAR
310	7508344.823	4696753.620	606.392	FS1
311	7508313.671	4696747.366	605.763	FS2
15	7508331.896	4696769.398	614.388	KULMI
16	7508341.921	4696777.843	610.163	KULMI
47	7508331.897	4696769.402	614.345	KULMI
48	7508340.241	4696772.611	610.143	KULMI
312	7508281.679	4696775.746	605.981	P1
313	7508281.679	4696775.746	605.981	P1
314	7508354.808	4696749.871	607.437	P2
315	7508354.808	4696749.871	607.437	P2
316	7508367.412	4696756.371	607.215	P3
317	7508367.412	4696756.371	607.215	P3
318	7508342.989	4696783.814	606.735	P4
2	7508341.840	4696777.923	606.713	PERDHESA
6	7508337.302	4696773.278	606.713	PERDHESA
17	7508329.215	4696780.387	606.713	PERDHESA
20	7508328.464	4696776.214	606.713	PERDHESA
21	7508327.58	4696776.37	606.713	PERDHESA
24	7508327.11	4696773.82	606.713	PERDHESA
25	7508328	4696773.67	606.713	PERDHESA

Nr	Y	X	H	DSC
35	7508340.865	4696772.544	606.713	PERDHESA
37	7508336.678	4696769.938	606.713	PERDHESA
38	7508336.362	4696769.982	606.713	PERDHESA
39	7508334.951	4696769.015	606.713	PERDHESA
40	7508333.108	4696769.414	606.713	PERDHESA
41	7508332.215	4696770.638	606.713	PERDHESA
43	7508331.794	4696770.895	606.713	PERDHESA
44	7508327.626	4696771.688	606.713	PERDHESA
52	7508279.855	4696772.393	605.657	PUSET-F
59	7508321.341	4696762.470	606.160	PUSET-F
183	7508326.910	4696783.942	605.737	PUSET-F
234	7508330.299	4696817.440	605.632	PUSET-F
241	7508321.277	4696820.681	605.480	PUSET-F
302	7508347.459	4696755.447	606.383	PUSET-F
309	7508320.663	4696758.260	605.102	PUSET-U
324	7508322.462	4696767.082	606.362	PUSET-U
56	7508289.457	4696773.423	605.713	SHTYLL-EL
65	7508326.520	4696763.787	606.284	SHTYLL-EL
89	7508356.025	4696746.112	607.295	SHTYLL-EL
93	7508360.710	4696757.200	606.998	SHTYLL-EL

Shpjegues:

- Kufiri kadastral (nga SIKTK-G)
- Ndërtesa në trajtim për legalizim
- Ndërtesa tjera
- Aneks Ndërtimi
- Shtyllë elektrike
- Pusetë e ujësjellësit
- Pusetë e ujërave të zeza
- Strehët
- Kyqje në rrymë
- Pikë e objekteve fqinje
- Rr. Emri i rrugës
- P4 Pikë e rrjetës gjeodezike
- 131 Pikë e strehëve
- Pikë e terasës
- 10 Pikë e objektit
- Pikë e murit
- 92 Pikë e kulmit

Rilevoi / Snimi: LIRIDON SEJDIU

(emri dhe mbiemri i gjedetit/kompanisë/ ime i prezime gedeta/ kompanije)

Nr. i licencës / Br. licence: 140

Data e rilevimit / Datum snimanja: 18.11.2023

Nënshkrimi / Potpis: _____

V.V.

Nr	Y	X	H	Kodi	Përshkrimi	Burimi
2	7508341.840	4696777.923	606.713	40	Shtëpi-Ndërtesë	PM
6	7508337.302	4696773.278	606.713	40	Shtëpi-Ndërtesë	PM
17	7508329.215	4696780.387	606.713	40	Shtëpi-Ndërtesë	PM
20	7508328.464	4696776.214	606.713	40	Shtëpi-Ndërtesë	PM
21	7508327.580	4696776.373	606.713	40	Shtëpi-Ndërtesë	PM
24	7508327.112	4696773.824	606.713	40	Shtëpi-Ndërtesë	PM
25	7508327.996	4696773.674	606.713	40	Shtëpi-Ndërtesë	PM
35	7508340.865	4696772.544	606.713	40	Shtëpi-Ndërtesë	PM
37	7508336.678	4696769.938	606.713	40	Shtëpi-Ndërtesë	PM
38	7508336.362	4696769.982	606.713	40	Shtëpi-Ndërtesë	PM
39	7508334.951	4696769.015	606.713	40	Shtëpi-Ndërtesë	PM
40	7508333.108	4696769.414	606.713	40	Shtëpi-Ndërtesë	PM
41	7508332.215	4696770.638	606.713	40	Shtëpi-Ndërtesë	PM
43	7508331.794	4696770.895	606.713	40	Shtëpi-Ndërtesë	PM
44	7508327.626	4696771.688	606.713	40	Shtëpi-Ndërtesë	PM

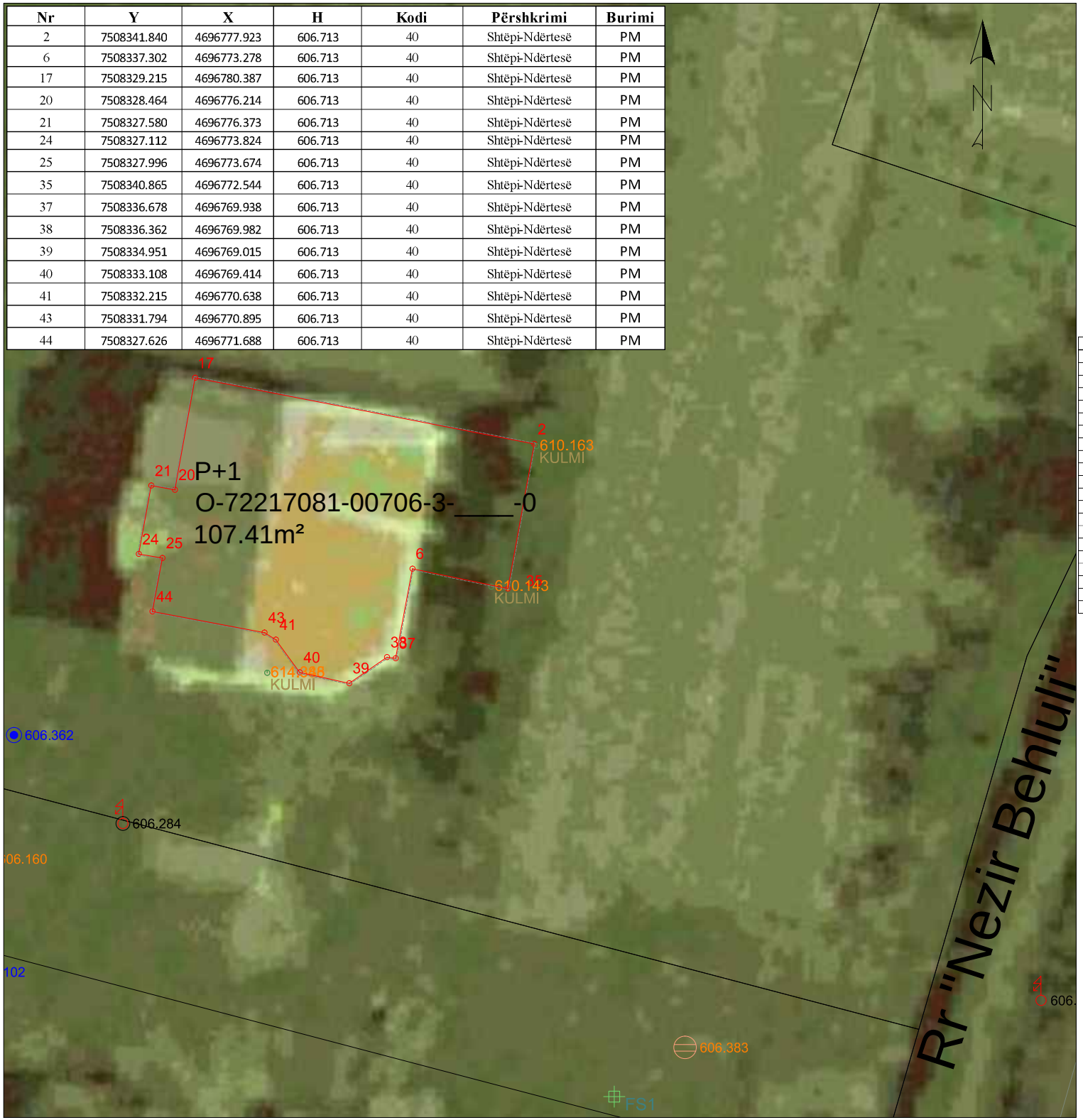

Republika e Kosovës

Qeveria -Vlada

Ministria e Mjedisit dhe Planifikimit Hapësinr /Ministarstv Sredine i Prstrng Planiranja

AGJENCIA KADASTRALE E KOSOVËS/ KATASTARSKA AGENCIJA KOSOVA

Situacioni i terrenit

Orto 2004

Zyra kadastrale kmunale / pštinska katastarska kancelarija: Ferizaj

Zona kadastrale / Katastarska zona: Slivovë

Nr. i njësisë kadastrale / Br. katastarske jedinice : 706-3

Numri i lëndës / Broj predmeta: _____

Shkalla e zvoglimit / Razmera plana 1: 200

Lista e koordinatave të pikave të matura:

Nr	Y	X	H	DSC
319	7508342.699	4696784.165	606.735	BUNAR
310	7508344.823	4696753.620	606.392	FS1
311	7508313.671	4696747.366	605.763	FS2
15	7508331.896	4696769.398	614.388	KULMI
16	7508341.921	4696777.843	610.163	KULMI
47	7508331.897	4696769.402	614.345	KULMI
48	7508340.241	4696772.611	610.143	KULMI
312	7508281.679	4696775.746	605.981	P1
313	7508281.679	4696775.746	605.981	P1
314	7508354.808	4696749.871	607.437	P2
315	7508354.808	4696749.871	607.437	P2
316	7508367.412	4696756.371	607.215	P3
317	7508367.412	4696756.371	607.215	P3
318	7508342.989	4696783.814	606.735	P4
2	7508341.840	4696777.923	606.713	PERDHESA
6	7508337.302	4696773.278	606.713	PERDHESA
17	7508329.215	4696780.387	606.713	PERDHESA
20	7508328.464	4696776.214	606.713	PERDHESA
21	7508327.58	4696776.37	606.713	PERDHESA
24	7508327.11	4696773.82	606.713	PERDHESA
25	7508328	4696773.67	606.713	PERDHESA

Nr	Y	X	H	DSC
35	7508340.865	4696772.544	606.713	PERDHESA
37	7508336.678	4696769.938	606.713	PERDHESA
38	7508336.362	4696769.982	606.713	PERDHESA
39	7508334.951	4696769.015	606.713	PERDHESA
40	7508333.108	4696769.414	606.713	PERDHESA
41	7508332.215	4696770.638	606.713	PERDHESA
43	7508331.794	4696770.895	606.713	PERDHESA
44	7508327.626	4696771.688	606.713	PERDHESA
52	7508279.855	4696772.393	605.657	PUSET-F
59	7508321.341	4696762.470	606.160	PUSET-F
183	7508326.910	4696783.942	605.737	PUSET-F
234	7508330.299	4696817.440	605.632	PUSET-F
241	7508321.277	4696820.681	605.480	PUSET-F
302	7508347.459	4696755.447	606.383	PUSET-F
309	7508320.663	4696758.260	605.102	PUSET-U
324	7508322.462	4696767.082	606.362	PUSET-U
56	7508289.457	4696773.423	605.713	SHTYLL-EL
65	7508326.520	4696763.787	606.284	SHTYLL-EL
89	7508356.025	4696746.112	607.295	SHTYLL-EL
93	7508360.710	4696757.200	606.998	SHTYLL-EL

Shpjegues:

- Kufiri kadastral (nga SIKTK-G)
- Ndërtesa në trajtim për legalizim
- Ndërtesa tjera
- Aneks Ndërtimi
- Shtyllë elektrike
- Pusetë e ujësjellësit
- Pusetë e ujërave të zeza
- Strehët
- Kyqje në rrymë
- Pikë e objekteve fqinje
- Rr. Emri i rrugës
- P4 Pikë e rrjetës gjeodezike
- 131 Pikë e strehëve
- Pikë e terasës
- 10 Pikë e objektit
- Pikë e murit
- 92 Pikë e kulmit

Rilevoi / Snimi: LIRIDON SEJDIU

(emri dhe mbiemri i gjedetit/kompanisë/ ime i prezime gedeta/ kompanije)

Nr. i licencës / Br. licence: 140

Data e rilevimit / Datum snimanja: 18.11.2023

Nënshkrimi / Potpis: _____

V.V.

Nr	Y	X	H	Kodi	Përshkrimi	Burimi
2	7508341.840	4696777.923	606.713	40	Shtëpi-Ndërtesë	PM
6	7508337.302	4696773.278	606.713	40	Shtëpi-Ndërtesë	PM
17	7508329.215	4696780.387	606.713	40	Shtëpi-Ndërtesë	PM
20	7508328.464	4696776.214	606.713	40	Shtëpi-Ndërtesë	PM
21	7508327.580	4696776.373	606.713	40	Shtëpi-Ndërtesë	PM
24	7508327.112	4696773.824	606.713	40	Shtëpi-Ndërtesë	PM
25	7508327.996	4696773.674	606.713	40	Shtëpi-Ndërtesë	PM
35	7508340.865	4696772.544	606.713	40	Shtëpi-Ndërtesë	PM
37	7508336.678	4696769.938	606.713	40	Shtëpi-Ndërtesë	PM
38	7508336.362	4696769.982	606.713	40	Shtëpi-Ndërtesë	PM
39	7508334.951	4696769.015	606.713	40	Shtëpi-Ndërtesë	PM
40	7508333.108	4696769.414	606.713	40	Shtëpi-Ndërtesë	PM
41	7508332.215	4696770.638	606.713	40	Shtëpi-Ndërtesë	PM
43	7508331.794	4696770.895	606.713	40	Shtëpi-Ndërtesë	PM
44	7508327.626	4696771.688	606.713	40	Shtëpi-Ndërtesë	PM

Republika e Kosovës

Qeveria -Vlada

Ministria e Mjedisit dhe Planifikimit Hapësinr /Ministarstv Sredine i Prstrng Planiranja

AGJENCIA KADASTRALE E KOSOVËS/ KATASTARSKA AGENCIJA KOSOVA

Situacioni i terrenit

Orto 2018

Zyra kadastrale kmunale / pštinska katastarska kancelarija: Ferizaj

Zona kadastrale / Katastarska zona: Slivovë

Nr. i njësisë kadastrale / Br. katastarske jedinice : 706-3

Numri i lëndës / Broj predmeta: _____

Shkalla e zvoglimit / Razmera plana 1: 200

Lista e koordinatave të pikave të matura:

Nr	Y	X	H	DSC
319	7508342.699	4696784.165	606.735	BUNAR
310	7508344.823	4696753.620	606.392	FS1
311	7508313.671	4696747.366	605.763	FS2
15	7508331.896	4696769.398	614.388	KULMI
16	7508341.921	4696777.843	610.163	KULMI
47	7508331.897	4696769.402	614.345	KULMI
48	7508340.241	4696772.611	610.143	KULMI
312	7508281.679	4696775.746	605.981	P1
313	7508281.679	4696775.746	605.981	P1
314	7508354.808	4696749.871	607.437	P2
315	7508354.808	4696749.871	607.437	P2
316	7508367.412	4696756.371	607.215	P3
317	7508367.412	4696756.371	607.215	P3
318	7508342.989	4696783.814	606.735	P4
2	7508341.840	4696777.923	606.713	PERDHESA
6	7508337.302	4696773.278	606.713	PERDHESA
17	7508329.215	4696780.387	606.713	PERDHESA
20	7508328.464	4696776.214	606.713	PERDHESA
21	7508327.58	4696776.37	606.713	PERDHESA
24	7508327.11	4696773.82	606.713	PERDHESA
25	7508328	4696773.67	606.713	PERDHESA

Nr	Y	X	H	DSC
35	7508340.865	4696772.544	606.713	PERDHESA
37	7508336.678	4696769.938	606.713	PERDHESA
38	7508336.362	4696769.982	606.713	PERDHESA
39	7508334.951	4696769.015	606.713	PERDHESA
40	7508333.108	4696769.414	606.713	PERDHESA
41	7508332.215	4696770.638	606.713	PERDHESA
43	7508331.794	4696770.895	606.713	PERDHESA
44	7508327.626	4696771.688	606.713	PERDHESA
52	7508279.855	4696772.393	605.657	PUSET-F
59	7508321.341	4696762.470	606.160	PUSET-F
183	7508326.910	4696783.942	605.737	PUSET-F
234	7508330.299	4696817.440	605.632	PUSET-F
241	7508321.277	4696820.681	605.480	PUSET-F
302	7508347.459	4696755.447	606.383	PUSET-F
309	7508320.663	4696758.260	605.102	PUSET-U
324	7508322.462	4696767.082	606.362	PUSET-U
56	7508289.457	4696773.423	605.713	SHTYLL-EL
65	7508326.520	4696763.787	606.284	SHTYLL-EL
89	7508356.025	4696746.112	607.295	SHTYLL-EL
93	7508360.710	4696757.200	606.998	SHTYLL-EL

Shpjegues:

- Kufiri kadastral (nga SIKTK-G)
- Ndërtesa në trajtim për legalizim
- Ndërtesa tjera
- Aneks Ndërtimi
- Shtyllë elektrike
- Pusetë e ujësjellësit
- Pusetë e ujërave të zeza
- Strehët
- Kyqje në rrymë
- Pikë e objekteve fqinje
- Rr. Emri i rrugës
- P4 Pikë e rrjetës gjeodezike
- 131 Pikë e strehëve
- Pikë e terasës
- 10 Pikë e objektit
- Pikë e murit
- 92 Pikë e kulmit

Rilevoi / Snimi: LIRIDON SEJDIU

(emri dhe mbiemri i gjedetit/kompanisë/ ime i prezime gedeta/ kompanije)

Nr. i licencës / Br. licence: 140

Data e rilevimit / Datum snimanja: 18.11.2023

Nënshkrimi / Potpis: _____

V.V.

Republika e Kosovës
Republika Kosova-Republic of Kosovo
Qeveria e Kosovës- Vlada Kosova- Government of Kosovo
Ministria e Infrastrukturës dhe Ambientit/ Ministrastvo Infrastrukture i Sredine/ Ministry of Infrastructure and Environment
AGJENCIA KADASTRALE E KOSOVËS/KOSOVSKA KATASTARSKA AGENCIJA/ KOSOVO CADASTRAL AGENCY

Komuna: Ferizaj	**Zona Kadastrale: Slivovë**
Numri i njësis kadastrale: 00706-3	**Sistemi koordinat: KosovaRef01**

Nr	Y	X	H	Kodi	Përshkrimi	Burimi
2	7508341.840	4696777.923	606.713	40	Shtëpi-Ndërtesë	PM
6	7508337.302	4696773.278	606.713	40	Shtëpi-Ndërtesë	PM
17	7508329.215	4696780.387	606.713	40	Shtëpi-Ndërtesë	PM
20	7508328.464	4696776.214	606.713	40	Shtëpi-Ndërtesë	PM
21	7508327.580	4696776.373	606.713	40	Shtëpi-Ndërtesë	PM
24	7508327.112	4696773.824	606.713	40	Shtëpi-Ndërtesë	PM
25	7508327.996	4696773.674	606.713	40	Shtëpi-Ndërtesë	PM
35	7508340.865	4696772.544	606.713	40	Shtëpi-Ndërtesë	PM
37	7508336.678	4696769.938	606.713	40	Shtëpi-Ndërtesë	PM
38	7508336.362	4696769.982	606.713	40	Shtëpi-Ndërtesë	PM
39	7508334.951	4696769.015	606.713	40	Shtëpi-Ndërtesë	PM
40	7508333.108	4696769.414	606.713	40	Shtëpi-Ndërtesë	PM
41	7508332.215	4696770.638	606.713	40	Shtëpi-Ndërtesë	PM
43	7508331.794	4696770.895	606.713	40	Shtëpi-Ndërtesë	PM
44	7508327.626	4696771.688	606.713	40	Shtëpi-Ndërtesë	PM

Gjeodeti / Kompania gjeodete e licencuar:	Liridon Sejdiu	Nënshkrimi dhe vula:	
Numri i licencës	140		

Kërko | Rezultati i kërkimit

Shfaq Zgjedhur Rezultatet Shkarko

ParcelDetailId	CadastreUnitId	CadastreZoneId	Ca
12388156	P-72217081-00...	72217081	72

Vendos në objekt | Zmadho në objekt

Numri i rezultateve: 1 (showing first 1)
Nga harta: 0

Detajet

ParcelDetailId:	12388156
CadastreUnitId:	P-72217081-00706-3
CadastreZoneId:	72217081
CadastreZoneCode:	72217081
Geometry:	
Status:	1
Sipërfaqja Grafike (m²):	2822.6

Raport

Lista e shtresës | Ndihma

- Ortofoto
  - Orthophoto2018Rural
  - Orthophoto2018Malore
  - Orthophoto2018Urban
  - Ortofoto 2015 UAV
  - Ortofoto 2012
  - Ortofoto 2009
  - Ortofoto 2004
  - Ortofoto 2001
- Hartat Topografike
  - Harta Topografike 1:250000
  - Harta Topografike 1:25000 (2015)
  - Nomenklatura
- Rilevimi
  - Indeksi i Ortofotove 2018
- Rrjeti Rrugor
  - Autostradë
  - Rrugë Nacionale
  - Rrugë Rajonale
- Njësi Administrative
  - Kufiri Shtetëror
  - Kufijtë dhe Emrat e Komunave
  - Zonë urbane
  - Zonat Postale
- Njësitë Kadastrale
  - Zonat Kadastrale
  - Parcelat
  - Numri parcelës
  - Ndërtesat
  - Numri ndërtesës
- Sistemi i Adresave
  - Rrugët
  - Emrat e rrugëve
  - Adresa
- Gjendja e Adresave ne Kosove
  - Adresat në gjeoportal
  - Emërtimi i rrugëve
  - Tabelat e emrave të rrugëve
  - Tabelat e numrave të adresave
- Gjeodetët e Licencuar
  - Gjeodetët
- Pasqyrimi i hartave kadastrale

1 : 500 | Auto | Shfaq këshillat | Kërko

KosovaRef01

Pozita: 7508328.400, 4696802.420

Kërko | **Rezultati i kërkimit**

Shfaq Zgjedhur Rezultatet Shkarko

	ParcelDetailId	CadastreUnitId	CadastreZoneId	Ca
☑	12388156	P-72217081-00...	72217081	72

◉ Vendos në objekt ○ Zmadho në objekt

Numri i rezultateve: 1 (showing first 1)
Nga harta: 0

Detajet

ParcelDetailId:	12388156
CadastreUnitId:	P-72217081-00706-3
CadastreZoneId:	217081
CadastreZoneCode:	72217081
Geometry:	
Status:	1
Sipërfaqja Grafike (m²):	2822.6

Raport

Lista e shtresës | Ndihma

- Ortofoto
  - ☑ Orthophoto2018Rural
  - ☑ Orthophoto2018Malore
  - ☑ Orthophoto2018Urban
  - ☐ Ortofoto 2015 UAV
  - ☐ Ortofoto 2012
  - ☐ Ortofoto 2009
  - ☐ Ortofoto 2004
  - ☐ Ortofoto 2001
- Hartat Topografike
  - Harta Topografike 1:250000
  - Harta Topografike 1:25000 (2015)
  - ☐ Nomenklatura
- Rilevimi
  - ☐ Indeksi i Ortofotove 2018
- Rrjeti Rrugor
  - ☑ Autostradë
  - ☑ Rrugë Nacionale
  - ☑ Rrugë Rajonale
- Njësi Administrative
  - ☐ Kufiri Shtetëror
  - Kufijtë dhe Emrat e Komunave
  - ☐ Zonë urbane
  - ☐ Zonat Postale
- Njësitë Kadastrale
  - ☑ Zonat Kadastrale
  - ☑ Parcelat
    - ☑ Numri parcelës
  - ☑ Ndërtesat
    - ☑ Numri ndërtesës
- Sistemi i Adresave
  - ☑ Rrugët
    - ☑ Emrat e rrugëve
  - ☑ Adresa
- Gjendja e Adresave ne Kosove
  - ☐ Adresat në gjeoportal
  - ☐ Emërtimi i rrugëve
  - ☐ Tabelat e emrave të rrugëve
  - ☐ Tabelat e numrave të adresave
- Gjeodetët e Licencuar
  - ☐ Gjeodetët
- Pasqyrimi i hartave kadastrale

1 : 500 | Auto | ☐ Shfaq kështillat | Kërko

KosovaRef01

Pozita: 7508328.820, 4696803.260

Zyra kadastrale komunale / Opštinska katastarska kancelarija: Ferizaj

Nr. i njësisë kadastrale / Br. katastarske jedinice : 706-3

Zona kadastrale / Katastarska zona: Slivovë

Numri i lëndës / Broj predmeta:

Lloji i njësisë kadastrale / Vrsta katastarske jedinice : Shtëpi

Shkalla e zvoglimit / Razmera plana 1: 150

Republika e Kosovës

Republika Kosova-Republic of Kosova

Qeveria -Vlada-Government

Ministria e Mjedisit dhe Planifikimit Hapësinor /Ministarstvo Sredine i Prostornog Planiranja/Ministry of Environment and Spatial Planning

AGJENCIA KADASTRALE E KOSOVËS/ KATASTARSKA AGECIJA KOSOVA/ KOSOVA CADASTRAL AGENCY

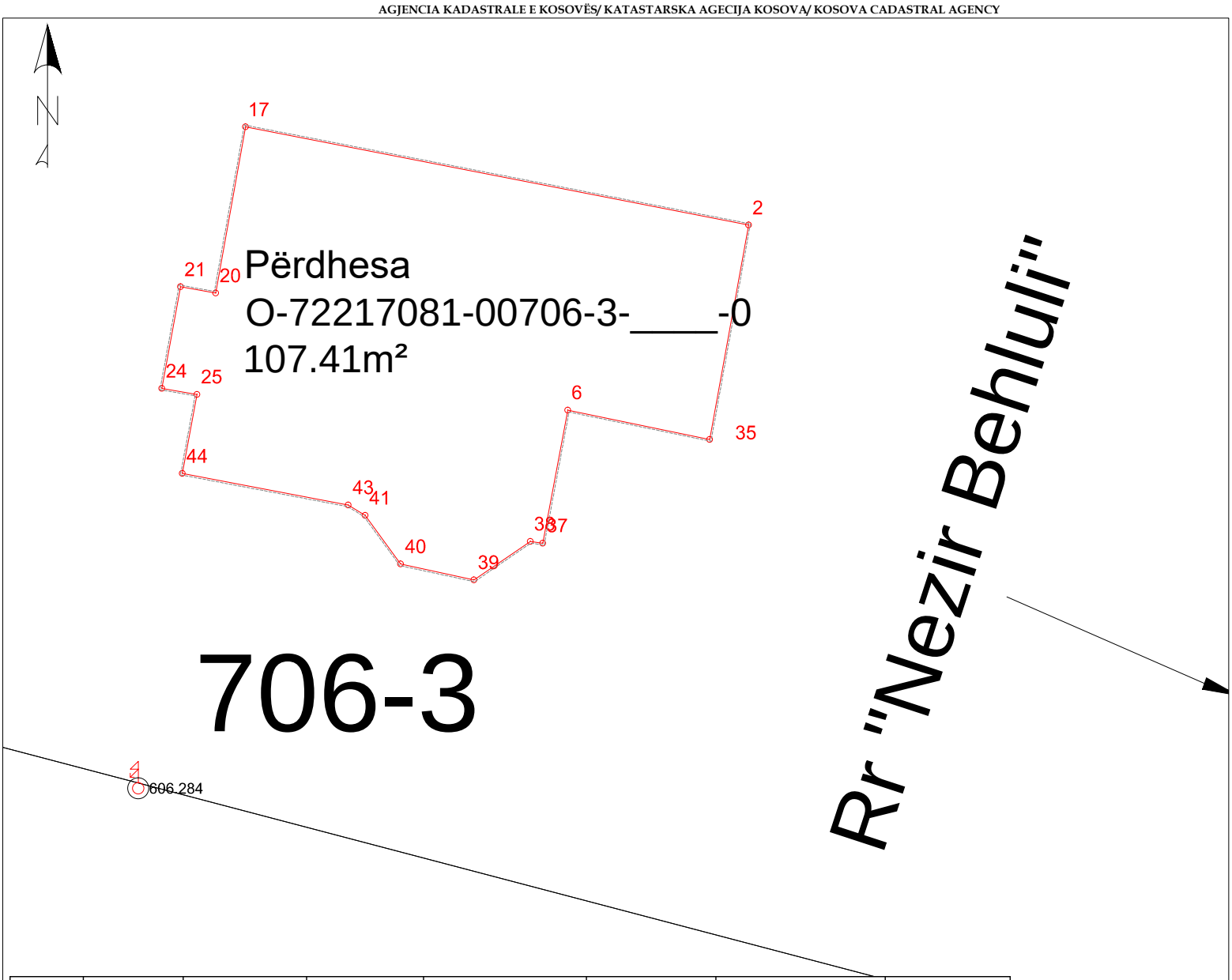

Nr.	Y	X	H	D	Etazhi	Sqarim	Sipërfaqja (m²)
2	7508341.84	4696777.92	606.71	PERDHESA	Përdhesa	Përdhesa	107.41
6	7508337.30	4696773.28	606.71	PERDHESA			
17	7508329.22	4696780.39	606.71	PERDHESA			
20	7508328.46	4696776.21	606.71	PERDHESA			
21	7508327.58	4696776.37	606.71	PERDHESA			
24	7508327.11	4696773.82	606.71	PERDHESA			
25	7508328.00	4696773.67	606.71	PERDHESA			
35	7508340.86	4696772.54	606.71	PERDHESA			
37	7508336.68	4696769.94	606.71	PERDHESA			
38	7508336.36	4696769.98	606.71	PERDHESA			
39	7508334.95	4696769.01	606.71	PERDHESA			
40	7508333.11	4696769.41	606.71	PERDHESA			
41	7508332.21	4696770.64	606.71	PERDHESA			
43	7508331.79	4696770.89	606.71	PERDHESA			
44	7508327.63	4696771.69	606.71	PERDHESA		**Gjithsej:**	**107.41**

Rilevoi / Snimio: LIRIDON SEJDIU

(emri dhe mbiemri i gjeodetit/kompanisë/ ime i prezime geodeta/ kompanije)

Nr. i licencës / Br. licence: 140

Nënshkrimi / Potpis:

Data e rilevimit / Datum snimanja: 18.11.2023

V.V.

Aprovoi / Usvojio:

(emri dhe mbiemri i përsonit zyrtar/ ime i prezime sluzbenog lica)

Nënshkrimi / Potpis:

Data e rilevimit / Datum snimanja:

Zyra kadastrale komunale / Opštinska katastarska kancelarija: Ferizaj

Nr. i njësisë kadastrale / Br. katastarske jedinice : 706-3

Zona kadastrale / Katastarska zona: Slivovë

Numri i lëndës / Broj predmeta:

Lloji i njësisë kadastrale / Vrsta katastarske jedinice : Shtëpi

Shkalla e zvoglimit / Razmera plana 1: 150

Republika e Kosovës

Republika Kosova-Republic of Kosova

Qeveria -Vlada-Government

Ministria e Mjedisit dhe Planifikimit Hapësinor /Ministarstvo Sredine i Prostornog Planiranja/Ministry of Environment and Spatial Planning

AGJENCIA KADASTRALE E KOSOVËS/ KATASTARSKA AGECIJA KOSOVA/ KOSOVA CADASTRAL AGENCY

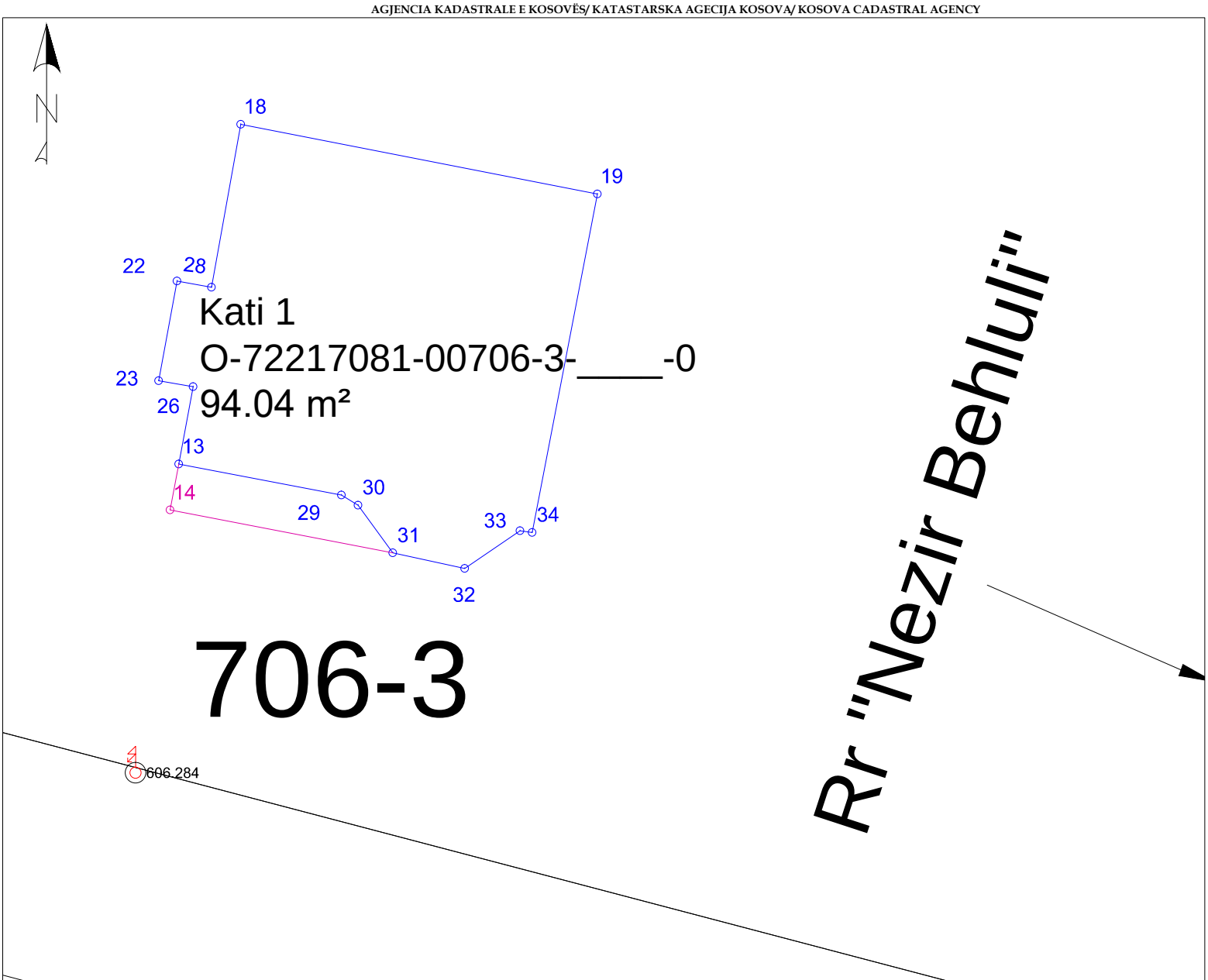

Nr.	Y	X	H	D	Etazhi	Sqarim	Sipërfaqja (m²)
13	7508327.63	4696771.69	609.58	KATI1	Kati 1	Kati 1	87.87
18	7508329.22	4696780.39	609.58	KATI1			
19	7508338.34	4696778.61	609.58	KATI1			
22	7508327.58	4696776.37	609.58	KATI1			
23	7508327.11	4696773.82	609.58	KATI1			
26	7508328.00	4696773.67	609.58	KATI1			
28	7508328.46	4696776.21	609.58	KATI1			
29	7508331.79	4696770.89	609.58	KATI1			
30	7508332.21	4696770.64	609.58	KATI1			
31	7508333.11	4696769.41	609.58	KATI1			
32	7508334.95	4696769.01	609.58	KATI1			
33	7508336.36	4696769.98	609.58	KATI1			
34	7508336.68	4696769.94	609.58	KATI1		Terasa	6.18
14	7508327.41	4696770.51	609.58	KATI1-TERASA		**Gjithsej:**	**94.04**

Rilevoi / Snimio: LIRIDON SEJDIU

(emri dhe mbiemri i gjeodetit/kompanisë/ ime i prezime geodeta/ kompanije)

Nr. i licencës / Br. licence: 140

Nënshkrimi / Potpis:

Data e rilevimit / Datum snimanja: 18.11.2023

V.V.

Aprovoi / Usvojio:

(emri dhe mbiemri i përsonit zyrtar/ ime i prezime sluzbenog lica)

Nënshkrimi / Potpis:

Data e rilevimit / Datum snimanja:

Republika e Kosovës
Republika Kosova-Republic of Kosovo
Qeveria e Kosovës- Vlada Kosova- Government of Kosovo
Ministria e Infrastrukturës dhe Ambientit/ Ministrastvo Infrastrukture i Sredine/ Ministry of Infrastructure and Environment
AGJENCIA KADASTRALE E KOSOVËS/KOSOVSKA KATASTARSKA AGENCIJA/ KOSOVO CADASTRAL AGENCY

Komuna: Ferizaj **Zona Kadastrale: Slivovë**
Numri i njësis kadastrale: 00706-3 **Sistemi koordinat: KosovaRef01**

Nr.	Y	X	H	D	Etazhi	Sqarim	Sipërfaqja (m²)
2	7508341.84	4696777.92	606.71	PERDHESA	Përdhesa	Përdhesa	107.41
6	7508337.30	4696773.28	606.71	PERDHESA			
17	7508329.22	4696780.39	606.71	PERDHESA			
20	7508328.46	4696776.21	606.71	PERDHESA			
21	7508327.58	4696776.37	606.71	PERDHESA			
24	7508327.11	4696773.82	606.71	PERDHESA			
25	7508328.00	4696773.67	606.71	PERDHESA			
35	7508340.86	4696772.54	606.71	PERDHESA			
37	7508336.68	4696769.94	606.71	PERDHESA			
38	7508336.36	4696769.98	606.71	PERDHESA			
39	7508334.95	4696769.01	606.71	PERDHESA			
40	7508333.11	4696769.41	606.71	PERDHESA			
41	7508332.21	4696770.64	606.71	PERDHESA			
43	7508331.79	4696770.89	606.71	PERDHESA			
44	7508327.63	4696771.69	606.71	PERDHESA		**Gjithsej:**	**107.41**

Nr.	Y	X	H	D	Etazhi	Sqarim	Sipërfaqja (m²)
13	7508327.63	4696771.69	609.58	KATI1	Kati 1	Kati 1	87.87
18	7508329.22	4696780.39	609.58	KATI1			
19	7508338.34	4696778.61	609.58	KATI1			
22	7508327.58	4696776.37	609.58	KATI1			
23	7508327.11	4696773.82	609.58	KATI1			
26	7508328.00	4696773.67	609.58	KATI1			
28	7508328.46	4696776.21	609.58	KATI1			
29	7508331.79	4696770.89	609.58	KATI1			
30	7508332.21	4696770.64	609.58	KATI1			
31	7508333.11	4696769.41	609.58	KATI1			
32	7508334.95	4696769.01	609.58	KATI1			
33	7508336.36	4696769.98	609.58	KATI1			
34	7508336.68	4696769.94	609.58	KATI1		Terasa	6.18
14	7508327.41	4696770.51	609.58	KATI1-TERASA		**Gjithsej:**	**94.04**

Gjeodeti / Kompania gjeodete e licencuar:	Liridon Sejdiu	Nënshkrimi dhe vula:	
Numri i licencës	140		

Zyra kadastrale komunale / Opštinska katastarska kancelarija: Ferizaj

Nr. i njësisë kadastrale / Br. katastarske jedinice : 706-3-___-0

Zona kadastrale / Katastarska zona: Slivovë

Numri i lëndës / Broj predmeta: _____

Lloji i njësisë kadastrale / Vrsta katastarske jedinice : Shtëpi

Shkalla e zvoglimit / Razmera plana 1: 150

Republika e Kosovës

Republika Kosova-Republic of Kosova

Qeveria -Vlada-Government

Ministria e Mjedisit dhe Planifikimit Hapësinor /Ministarstvo Sredine i Prostornog Planiranja/Ministry of Environment and Spatial Planning

AGJENCIA KADASTRALE E KOSOVËS/ KATASTARSKA AGECIJA KOSOVA/ KOSOVA CADASTRAL AGENCY

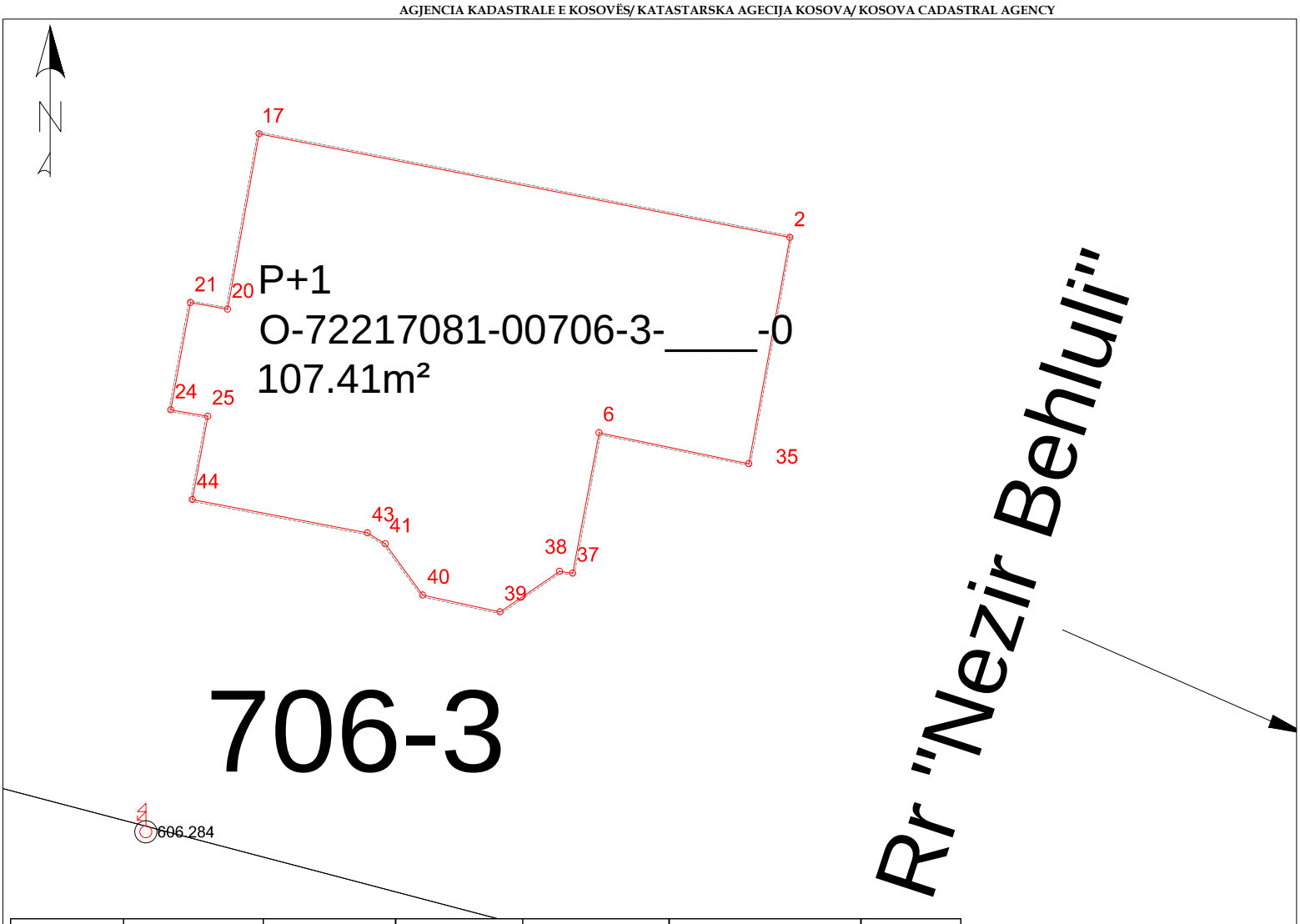

Nr	Y	X	H	Kodi	Përshkrimi	Burimi
2	7508341.840	4696777.923	606.713	40	Shtëpi-Ndërtesë	PM
6	7508337.302	4696773.278	606.713	40	Shtëpi-Ndërtesë	PM
17	7508329.215	4696780.387	606.713	40	Shtëpi-Ndërtesë	PM
20	7508328.464	4696776.214	606.713	40	Shtëpi-Ndërtesë	PM
21	7508327.580	4696776.373	606.713	40	Shtëpi-Ndërtesë	PM
24	7508327.112	4696773.824	606.713	40	Shtëpi-Ndërtesë	PM
25	7508327.996	4696773.674	606.713	40	Shtëpi-Ndërtesë	PM
35	7508340.865	4696772.544	606.713	40	Shtëpi-Ndërtesë	PM
37	7508336.678	4696769.938	606.713	40	Shtëpi-Ndërtesë	PM
38	7508336.362	4696769.982	606.713	40	Shtëpi-Ndërtesë	PM
39	7508334.951	4696769.015	606.713	40	Shtëpi-Ndërtesë	PM
40	7508333.108	4696769.414	606.713	40	Shtëpi-Ndërtesë	PM
41	7508332.215	4696770.638	606.713	40	Shtëpi-Ndërtesë	PM
43	7508331.794	4696770.895	606.713	40	Shtëpi-Ndërtesë	PM
44	7508327.626	4696771.688	606.713	40	Shtëpi-Ndërtesë	PM

Rilevoi / Snimio: LIRIDON SEJDIU
(emri dhe mbiemri i gjeodetit/kompanisë/ ime i prezime geodeta/ kompanije)

Nr. i licencës / Br. licence: 140

Nënshkrimi / Potpis: _____

Data e rilevimit / Datum snimanja: 18.11.2023

V.V.

Aprovoi / Usvojio: _____
(emri dhe mbiemri i përsonit zyrtar/ ime i prezime sluzbenog lica)

Nënshkrimi / Potpis: _____

Data e rilevimit / Datum snimanja: _____

Republika e Kosovës
Republika Kosova-Republic of Kosovo
Qeveria e Kosovës- Vlada Kosova- Government of Kosovo
Ministria e Infrastrukturës dhe Ambientit/ Ministrastvo Infrastrukture i Sredine/ Ministry of Infrastructure and Environment
AGJENCIA KADASTRALE E KOSOVËS/KOSOVSKA KATASTARSKA AGENCIJA/ KOSOVO CADASTRAL AGENCY

Komuna: Ferizaj	**Zona Kadastrale: Slivovë**
Numri i njësis kadastrale: 00706-3	**Sistemi koordinat: KosovaRef01**

Nr	Y	X	H	Kodi	Përshkrimi	Burimi
2	7508341.840	4696777.923	606.713	40	Shtëpi-Ndërtesë	PM
6	7508337.302	4696773.278	606.713	40	Shtëpi-Ndërtesë	PM
17	7508329.215	4696780.387	606.713	40	Shtëpi-Ndërtesë	PM
20	7508328.464	4696776.214	606.713	40	Shtëpi-Ndërtesë	PM
21	7508327.580	4696776.373	606.713	40	Shtëpi-Ndërtesë	PM
24	7508327.112	4696773.824	606.713	40	Shtëpi-Ndërtesë	PM
25	7508327.996	4696773.674	606.713	40	Shtëpi-Ndërtesë	PM
35	7508340.865	4696772.544	606.713	40	Shtëpi-Ndërtesë	PM
37	7508336.678	4696769.938	606.713	40	Shtëpi-Ndërtesë	PM
38	7508336.362	4696769.982	606.713	40	Shtëpi-Ndërtesë	PM
39	7508334.951	4696769.015	606.713	40	Shtëpi-Ndërtesë	PM
40	7508333.108	4696769.414	606.713	40	Shtëpi-Ndërtesë	PM
41	7508332.215	4696770.638	606.713	40	Shtëpi-Ndërtesë	PM
43	7508331.794	4696770.895	606.713	40	Shtëpi-Ndërtesë	PM
44	7508327.626	4696771.688	606.713	40	Shtëpi-Ndërtesë	PM

Gjeodeti / Kompania gjeodete e licencuar:	Liridon Sejdiu	Nënshkrimi dhe vula:	
Numri i licencës	140		

Republika e Kosovës
Republika Kosova - Republic of Kosovo
Qeveria e Kosovës - Vlada Kosova - Government of Kosovo
Ministria e Infrastrukturës dhe Ambientit/ Ministrastvo Infrastrukture i Sredine/ Ministry of Infrastructure and Environment
AGJENCIA KADASTRALE E KOSOVËS/ KOSOVSKA KATASTARSKA AGENCIJA/ KOSOVA CADASTRAL AGENCY

R E G J I S T R I M I I NDERTESËS / SHTËPISË

Nr	Komuna	Zona Kadastrale	Numri i ndërtesës (njësia)	Etazhiteti	Katet	Sipërfaqja e kateve [m²]	Sipërfaqja e bazamentit [m²]	Adresa e Njësisë	Vendi i quajtur	Shfrytëzimi i aktual	Pronari / Shfrytëzuesi Emri (Emri i prindit) Mbiemri	Numri përsonal	Pjesa e Pronës
1	Ferizaj	Slivovë	O-72217081-00706-3-____-0	P+1	Përdhesa	107.41	107.41	Rr."Nezir Behluli" Fsh. Slivovë- Ferizaj	PJESË E KOPSHTIT	Banim	Asllan (Adem) Sejdiu	1006885914	1/1
					Kati 1	94.04							
					Gjithsej:	**201.45**							

Gjeodeti/kompania e licencuar: LIRIDON SEJDIU	Nr i licencës: 140	Nënshkrimi dhe vula:

Zyra kadastrale komunale / Opštinska katastarska kancelarija: Ferizaj

Nr. i njësisë kadastrale / Br. katastarske jedinice : 706-3-___-0

Zona kadastrale / Katastarska zona: Slivovë

Numri i lëndës / Broj predmeta: _____

Lloji i njësisë kadastrale / Vrsta katastarske jedinice : Shtëpi

Shkalla e zvoglimit / Razmera plana 1: 150

Republika e Kosovës

Republika Kosova-Republic of Kosova

Qeveria -Vlada-Government

Ministria e Mjedisit dhe Planifikimit Hapësinor /Ministarstvo Sredine i Prostornog Planiranja/Ministry of Environment and Spatial Planning

AGJENCIA KADASTRALE E KOSOVËS/ KATASTARSKA AGECIJA KOSOVA/ KOSOVA CADASTRAL AGENCY

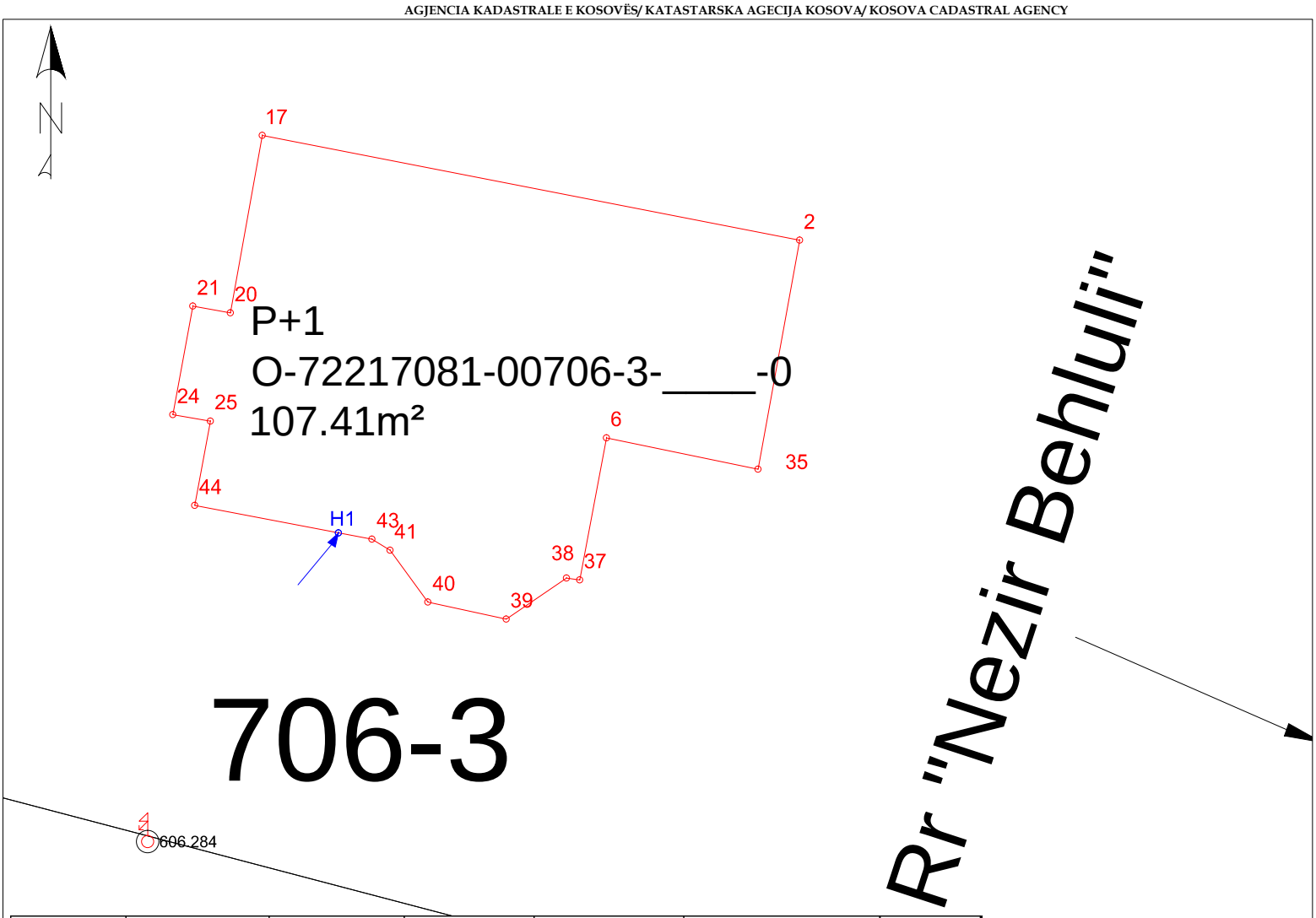

Nr	Y	X	H	Kodi	Përshkrimi	Burimi
2	7508341.840	4696777.923	606.713	40	Shtëpi-Ndërtesë	PM
6	7508337.302	4696773.278	606.713	40	Shtëpi-Ndërtesë	PM
17	7508329.215	4696780.387	606.713	40	Shtëpi-Ndërtesë	PM
20	7508328.464	4696776.214	606.713	40	Shtëpi-Ndërtesë	PM
21	7508327.580	4696776.373	606.713	40	Shtëpi-Ndërtesë	PM
24	7508327.112	4696773.824	606.713	40	Shtëpi-Ndërtesë	PM
25	7508327.996	4696773.674	606.713	40	Shtëpi-Ndërtesë	PM
35	7508340.865	4696772.544	606.713	40	Shtëpi-Ndërtesë	PM
37	7508336.678	4696769.938	606.713	40	Shtëpi-Ndërtesë	PM
38	7508336.362	4696769.982	606.713	40	Shtëpi-Ndërtesë	PM
39	7508334.951	4696769.015	606.713	40	Shtëpi-Ndërtesë	PM
40	7508333.108	4696769.414	606.713	40	Shtëpi-Ndërtesë	PM
41	7508332.215	4696770.638	606.713	40	Shtëpi-Ndërtesë	PM
43	7508331.794	4696770.895	606.713	40	Shtëpi-Ndërtesë	PM
44	7508327.626	4696771.688	606.713	40	Shtëpi-Ndërtesë	PM
325	7508331.008	4696771.045	606.713	40	Shtëpi-Ndërtesë	PM

Rilevoi / Snimio: LIRIDON SEJDIU
(emri dhe mbiemri i gjeodetit/kompanisë/ ime i prezime geodeta/ kompanije)

Nr. i licencës / Br. licence: 140

Nënshkrimi / Potpis: _____

Data e rilevimit / Datum snimanja: 18.11.2023

V.V.

Aprovoi / Usvojio: _____
(emri dhe mbiemri i përsonit zyrtar/ ime i prezime sluzbenog lica)

Nënshkrimi / Potpis: _____

Data e rilevimit / Datum snimanja: _____

Zyra kadastrale komunale / Opštinska katastarska kancelarija: Ferizaj

Nr. i njësisë kadastrale / Br. katastarske jedinice : 706-3-___-0

Zona kadastrale / Katastarska zona: Slivovë

Numri i lëndës / Broj predmeta: _____

Lloji i njësisë kadastrale / Vrsta katastarske jedinice : Pjesë e Shtëpisë

Shkalla e zvoglimit / Razmera plana 1: 150

Republika e Kosovës

Republika Kosova-Republic of Kosova

Qeveria -Vlada-Government

Ministria e Mjedisit dhe Planifikimit Hapësinor /Ministarstvo Sredine i Prostornog Planiranja/Ministry of Environment and Spatial Planning

AGJENCIA KADASTRALE E KOSOVËS/ KATASTARSKA AGECIJA KOSOVA/ KOSOVA CADASTRAL AGENCY

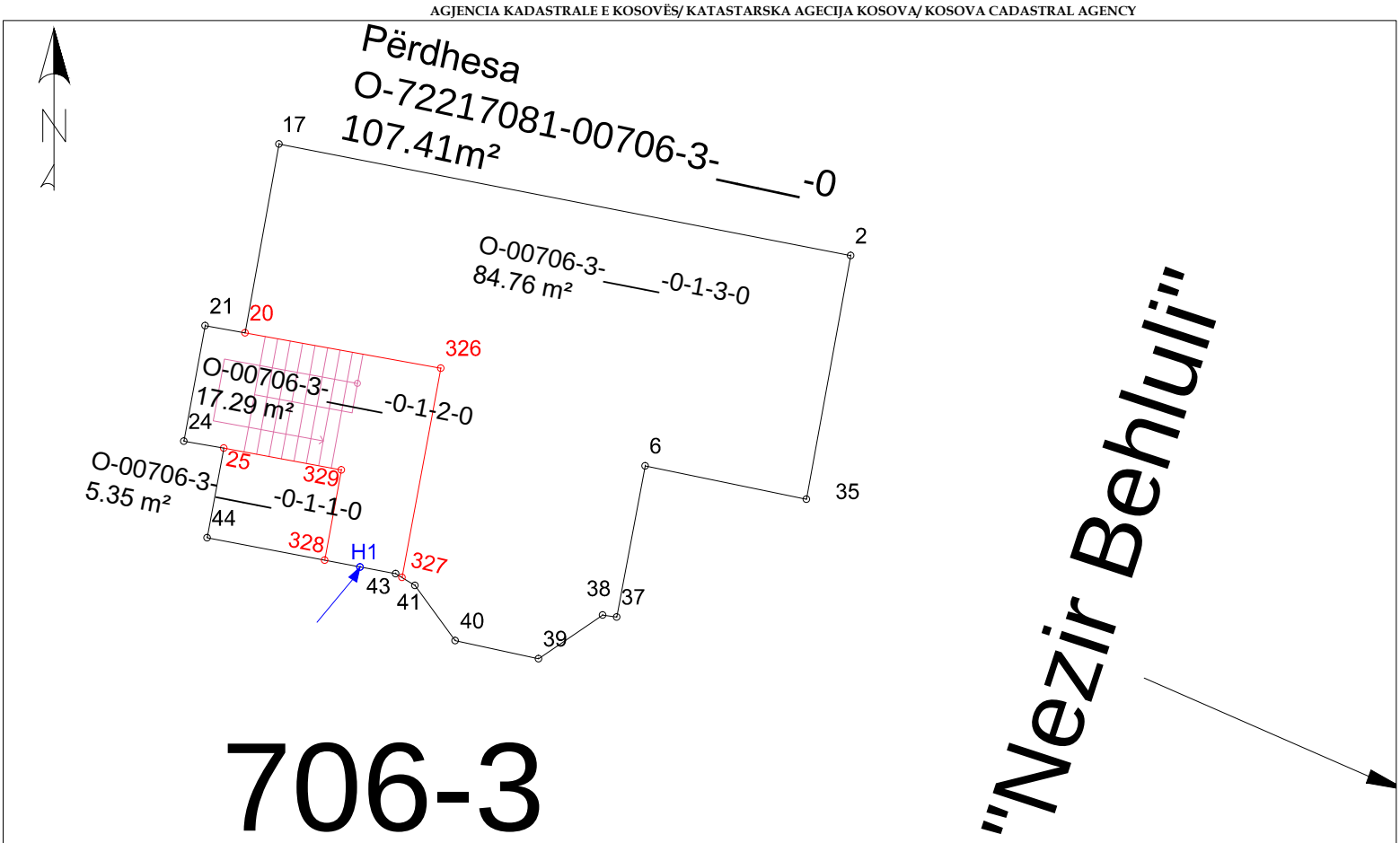

Nr	Y	X	h	Etazhi	Përshkrimi
2	7508341.84	4696777.92	606.713	Përdhesa	Pjesë e ndërteses
6	7508337.30	4696773.28			Pjesë e ndërteses
17	7508329.22	4696780.39			Pjesë e ndërteses
20	7508328.46	4696776.21			Pjesë e ndërteses
21	7508327.58	4696776.37			Pjesë e ndërteses
24	7508327.11	4696773.82			Pjesë e ndërteses
25	7508328.00	4696773.67			Pjesë e ndërteses
35	7508340.86	4696772.54			Pjesë e ndërteses
37	7508336.68	4696769.94			Pjesë e ndërteses
38	7508336.36	4696769.98			Pjesë e ndërteses
39	7508334.95	4696769.01			Pjesë e ndërteses
40	7508333.11	4696769.41			Pjesë e ndërteses
41	7508332.21	4696770.64			Pjesë e ndërteses
43	7508331.79	4696770.89			Pjesë e ndërteses
44	7508327.63	4696771.69			Pjesë e ndërteses
326	7508332.79	4696775.43			Pjesë e ndërteses
327	7508331.93	4696770.81			Pjesë e ndërteses
328	7508330.22	4696771.19			Pjesë e ndërteses
329	7508330.59	4696773.19			Pjesë e ndërteses
325	7508331.01	4696771.04			Pjesë e ndërteses

Rilevoi / Snimio: LIRIDON SEJDIU

(emri dhe mbiemri i gjeodetit/kompanisë/ ime i prezime geodeta/ kompanije)

Nr. i licencës / Br. licence: 140

Nënshkrimi / Potpis: _____

Data e rilevimit / Datum snimanja: 18.11.2023

V.V.

Aprovoi / Usvojio: _____

(emri dhe mbiemri i përsonit zyrtar/ ime i prezime sluzbenog lica)

Nënshkrimi / Potpis: _____

Data e rilevimit / Datum snimanja: _____

Zyra kadastrale komunale / Opštinska katastarska kancelarija: Ferizaj

Nr. i njësisë kadastrale / Br. katastarske jedinice : 706-3-___-0

Zona kadastrale / Katastarska zona: Slivovë

Numri i lëndës / Broj predmeta: _____

Lloji i njësisë kadastrale / Vrsta katastarske jedinice : Pjesë e Shtëpisë

Shkalla e zvoglimit / Razmera plana 1: 150

Republika e Kosovës

Republika Kosova-Republic of Kosova

Qeveria -Vlada-Government

Ministria e Mjedisit dhe Planifikimit Hapësinor /Ministarstvo Sredine i Prostornog Planiranja/Ministry of Environment and Spatial Planning

AGJENCIA KADASTRALE E KOSOVËS/ KATASTARSKA AGECIJA KOSOVA/ KOSOVA CADASTRAL AGENCY

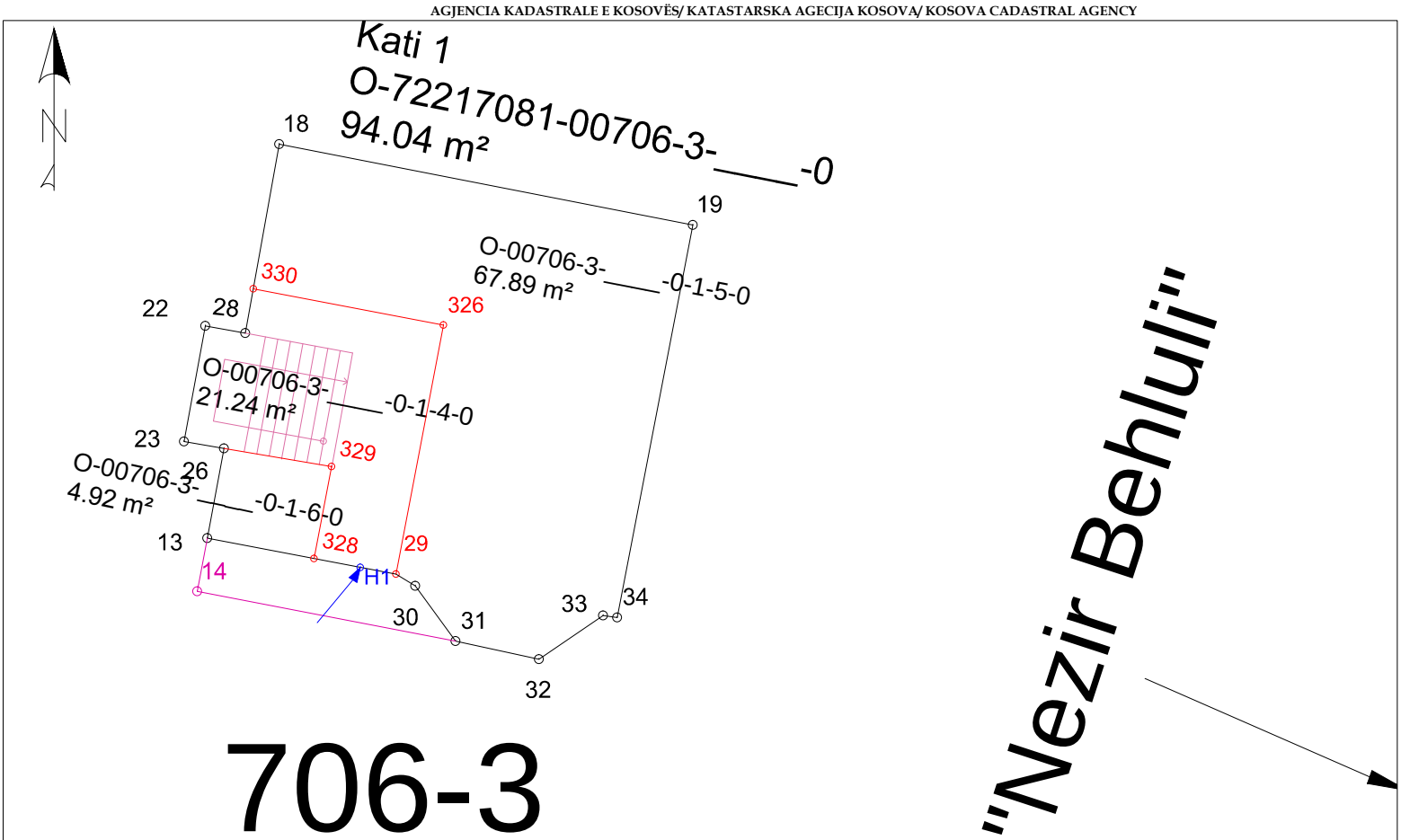

Nr	Y	X	h	Etazhi	Përshkrimi
326	7508332.84	4696776.40	609.583	KATI1	Pjesë e ndërteses
328	7508329.99	4696771.24			Pjesë e ndërteses
329	7508330.37	4696773.27			Pjesë e ndërteses
330	7508328.64	4696777.20			Pjesë e ndërteses
14	7508327.41	4696770.51			Pjesë e ndërteses
13	7508327.63	4696771.69			Pjesë e ndërteses
18	7508329.22	4696780.39			Pjesë e ndërteses
19	7508338.34	4696778.61			Pjesë e ndërteses
22	7508327.58	4696776.37			Pjesë e ndërteses
23	7508327.11	4696773.82			Pjesë e ndërteses
26	7508328.00	4696773.67			Pjesë e ndërteses
28	7508328.46	4696776.21			Pjesë e ndërteses
29	7508331.79	4696770.89			Pjesë e ndërteses
30	7508332.21	4696770.64			Pjesë e ndërteses
31	7508333.11	4696769.41			Pjesë e ndërteses
32	7508334.95	4696769.01			Pjesë e ndërteses
33	7508336.36	4696769.98			Pjesë e ndërteses
34	7508336.68	4696769.94			Pjesë e ndërteses
325	7508331.01	4696771.04			Pjesë e ndërteses

Rilevoi / Snimio: LIRIDON SEJDIU

(emri dhe mbiemri i gjeodetit/kompanisë/ ime i prezime geodeta/ kompanije)

Nr. i licencës / Br. licence: 140

Nënshkrimi / Potpis: _____

Data e rilevimit / Datum snimanja: 18.11.2023

V.V.

Aprovoi / Usvojio: _____

(emri dhe mbiemri i përsonit zyrtar/ ime i prezime sluzbenog lica)

Nënshkrimi / Potpis: _____

Data e rilevimit / Datum snimanja: _____

Republika e Kosovës
Republika Kosova-Republic of Kosovo
Qeveria e Kosovës- Vlada Kosova- Government of Kosovo
Ministria e Infrastrukturës dhe Ambientit/ Ministrastvo Infrastrukture i Sredine/ Ministry of Infrastructure and Environment
AGJENCIA KADASTRALE E KOSOVËS/KOSOVSKA KATASTARSKA AGENCIJA/ KOSOVO CADASTRAL AGENCY

Komuna: Ferizaj	**Zona Kadastrale: Slivovë**
Numri i njësis kadastrale: 00706-3	**Sistemi koordinat: KosovaRef01**

Nr	Y	X	H	Kodi	Përshkrimi	Burimi
2	7508341.840	4696777.923	606.713	40	Shtëpi-Ndërtesë	PM
6	7508337.302	4696773.278	606.713	40	Shtëpi-Ndërtesë	PM
17	7508329.215	4696780.387	606.713	40	Shtëpi-Ndërtesë	PM
20	7508328.464	4696776.214	606.713	40	Shtëpi-Ndërtesë	PM
21	7508327.580	4696776.373	606.713	40	Shtëpi-Ndërtesë	PM
24	7508327.112	4696773.824	606.713	40	Shtëpi-Ndërtesë	PM
25	7508327.996	4696773.674	606.713	40	Shtëpi-Ndërtesë	PM
35	7508340.865	4696772.544	606.713	40	Shtëpi-Ndërtesë	PM
37	7508336.678	4696769.938	606.713	40	Shtëpi-Ndërtesë	PM
38	7508336.362	4696769.982	606.713	40	Shtëpi-Ndërtesë	PM
39	7508334.951	4696769.015	606.713	40	Shtëpi-Ndërtesë	PM
40	7508333.108	4696769.414	606.713	40	Shtëpi-Ndërtesë	PM
41	7508332.215	4696770.638	606.713	40	Shtëpi-Ndërtesë	PM
43	7508331.794	4696770.895	606.713	40	Shtëpi-Ndërtesë	PM
44	7508327.626	4696771.688	606.713	40	Shtëpi-Ndërtesë	PM
325	7508331.008	4696771.045	606.713	40	Shtëpi-Ndërtesë	PM

Nr	Y	X	h	Etazhi	Përshkrimi
2	7508341.84	4696777.92	606.713	Përdhesa	Pjesë e ndërteses
6	7508337.30	4696773.28			Pjesë e ndërteses
17	7508329.22	4696780.39			Pjesë e ndërteses
20	7508328.46	4696776.21			Pjesë e ndërteses
21	7508327.58	4696776.37			Pjesë e ndërteses
24	7508327.11	4696773.82			Pjesë e ndërteses
25	7508328.00	4696773.67			Pjesë e ndërteses
35	7508340.86	4696772.54			Pjesë e ndërteses
37	7508336.68	4696769.94			Pjesë e ndërteses
38	7508336.36	4696769.98			Pjesë e ndërteses
39	7508334.95	4696769.01			Pjesë e ndërteses
40	7508333.11	4696769.41			Pjesë e ndërteses
41	7508332.21	4696770.64			Pjesë e ndërteses
43	7508331.79	4696770.89			Pjesë e ndërteses
44	7508327.63	4696771.69			Pjesë e ndërteses
326	7508332.79	4696775.43			Pjesë e ndërteses
327	7508331.93	4696770.81			Pjesë e ndërteses
328	7508330.22	4696771.19			Pjesë e ndërteses
329	7508330.59	4696773.19			Pjesë e ndërteses
325	7508331.01	4696771.04			Pjesë e ndërteses

Gjeodeti / Kompania gjeodete e licencuar:	Liridon Sejdiu	Nënshkrimi dhe vula:	
Numri i licencës	140		

Republika e Kosovës
Republika Kosova-Republic of Kosovo
Qeveria e Kosovës- Vlada Kosova- Government of Kosovo
Ministria e Infrastrukturës dhe Ambientit/ Ministrastvo Infrastrukture i Sredine/ Ministry of Infrastructure and Environment

Komuna: Ferizaj	**Zona Kadastrale: Slivovë**
Numri i njësis kadastrale: 00706-3	**Sistemi koordinat: KosovaRef01**

Nr	Y	X	h	Etazhi	Përshkrimi
326	7508332.84	4696776.40			Pjesë e ndërteses
328	7508329.99	4696771.24			Pjesë e ndërteses
329	7508330.37	4696773.27			Pjesë e ndërteses
330	7508328.64	4696777.20			Pjesë e ndërteses
14	7508327.41	4696770.51			Pjesë e ndërteses
13	7508327.63	4696771.69			Pjesë e ndërteses
18	7508329.22	4696780.39			Pjesë e ndërteses
19	7508338.34	4696778.61			Pjesë e ndërteses
22	7508327.58	4696776.37			Pjesë e ndërteses
23	7508327.11	4696773.82	609.583	KATI1	Pjesë e ndërteses
26	7508328.00	4696773.67			Pjesë e ndërteses
28	7508328.46	4696776.21			Pjesë e ndërteses
29	7508331.79	4696770.89			Pjesë e ndërteses
30	7508332.21	4696770.64			Pjesë e ndërteses
31	7508333.11	4696769.41			Pjesë e ndërteses
32	7508334.95	4696769.01			Pjesë e ndërteses
33	7508336.36	4696769.98			Pjesë e ndërteses
34	7508336.68	4696769.94			Pjesë e ndërteses
325	7508331.01	4696771.04			Pjesë e ndërteses

Koordinatat janë gjeneruar pas pozicionimit të pjesëve të ndertesës në sistem koordinat Kosovaref01

Gjeodeti / Kompania gjeodete e licencuar:	Liridon Sejdiu	Nënshkrimi dhe vula:	
Numri i licencës	140		

Republika e Kosovës

Republika Kosova-Republic of Kosova

Qeveria -Vlada-Government

Ministria e Infrastrukturës dhe Ambientit /Ministarstvo Infrastrukture i Sredine / Ministry of Infrastructure and Environment

AGJENCIA KADASTRALE E KOSOVËS/ KATASTARSKA AGENCIJA KOSOVA/ KOSOVA CADASTRAL AGENCY

R E G J I S T R I I P J E S Ë V E T Ë N D Ë R T E S Ë S

Gjeodeti apo kompania gjeodete e licencuar: LIRIDON SEJDIU numri i licencës: 140

Nr	Komuna	Zona Kadastrale	Numri i ndërtesës	Sipërfaqja [m²]	Lloji i Ndërtesës	Adresa e Ndërtesës	Vendi i quajtur	Leja e ndertimit	Pronari / Shfrytëzuesi	Numri personal	Adresa e pronarit	Pjesa e Pronësisë
1	Ferizaj	Slivovë	00706-3-_____-0	107.41	Shtëpi	Rr."Nezir Behluli",	PJESË E KOPSHTIT	JO	Asllan (Adem) Sejdiu	1006885914	fsh. Slivovë-Ferizaj	1/1

N D Ë R T E S A 00173-4-_____-0

Nr	Numri i njësisë pjesë e ndërtesës	Hyrja	Kati	Sipërfaqja [m²]	Adresa e Njësisë	Numri i adresës	Vendi i quajtur	Shfrytëzimi i aktual	Pronari / Shfrytëzuesi *Emri (Emri i prindit) Mbiemri*	Numri përsonal	Pjesa e Pronësis	Adresa e pronarit
1	O-00706-3-____-0-1-1-0	1	P	5.35	Rr."Nezir Behluli"	-	PJESË E KOPSHTIT	Banim	Asllan (Adem) Sejdiu	1006885914	1/1	fsh. Slivovë-Ferizaj
2	O-00706-3-____-0-1-2-0	1	P	17.29	Rr."Nezir Behluli"	-	PJESË E KOPSHTIT	Banim	Asllan (Adem) Sejdiu	1006885914	1/1	fsh. Slivovë-Ferizaj
3	O-00706-3-____-0-1-3-0	1	P	84.76	Rr."Nezir Behluli"	-	PJESË E KOPSHTIT	Banim	Asllan (Adem) Sejdiu	1006885914	1/1	fsh. Slivovë-Ferizaj
4	O-00706-3-____-0-1-4-0	1	1	21.24	Rr."Nezir Behluli"	-	PJESË E KOPSHTIT	Banim	Asllan (Adem) Sejdiu	1006885914	1/1	fsh. Slivovë-Ferizaj
5	O-00706-3-____-0-1-5-0	1	1	67.89	Rr."Nezir Behluli"	-	PJESË E KOPSHTIT	Banim	Asllan (Adem) Sejdiu	1006885914	1/1	fsh. Slivovë-Ferizaj
6	O-00706-3-____-0-1-6-0	1	1	4.92	Rr."Nezir Behluli"	-	PJESË E KOPSHTIT	Banim	Asllan (Adem) Sejdiu	1006885914	1/1	fsh. Slivovë-Ferizaj